INFORME TÉCNICO PREMIUM

Atlas de *Parcelas*

Preparado para: Cooperativa Agrícola Demo

Campaña MMXXV | Copernicus Sentinel-2 L2A | 22/04/2026

1 — LOCALIZACIÓN

Contexto Geográfico e IGN

ORTOFOTO PNOA

DELIMITACIÓN SIGPAC

MAPA TOPOGRÁFICO

ALTITUD	PENDIENTE	SUPERFICIE
450 m	*4.5%*	*3.68 ha*
ORIENTACIÓN	MUNICIPIO / POLÍGONO	
Sureste (SE)	*Logroño - 12/45*	

2 — ÍNDICES DE VEGETACIÓN

Estado del Cultivo

VIGOR (NDVI)



CLOROFILA (NDRE)

HUMEDAD (NDMI)

CALENDARIO DE DISPONIBILIDAD

Índice	Abr	May	Jun	Jul	Ago	Sep
NDVI	◑	●	●	●	●	◑
NDMI	○	◑	●	●	●	◑

3 — ANÁLISIS TEMPORAL

Evolución de la Campaña

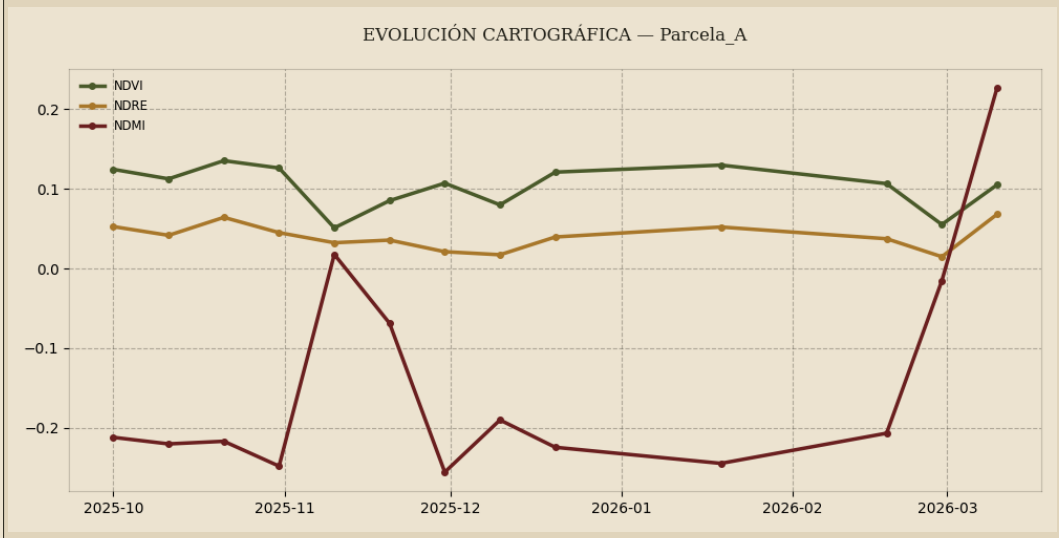

EVOLUCIÓN DE ÍNDICES MMXXV

4 — INTERPRETACIÓN Y RECOMENDACIONES

Dictamen Técnico

ESTADO ACTUAL
Óptimo

TENDENCIA
Estable

Estado vegetativo excelente. Se recomienda mantener monitorización.

1 — LOCALIZACIÓN

Contexto Geográfico e IGN

ORTOFOTO PNOA

DELIMITACIÓN SIGPAC

MAPA TOPOGRÁFICO

ALTITUD	PENDIENTE	SUPERFICIE
450 m	*4.5%*	*3.68 ha*
ORIENTACIÓN	MUNICIPIO / POLÍGONO	
Sureste (SE)	*Logroño - 14/02*	

2 — ÍNDICES DE VEGETACIÓN

Estado del Cultivo

VIGOR (NDVI)

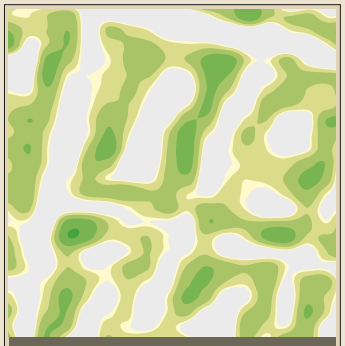

CLOROFILA (NDRE)

HUMEDAD (NDMI)

CALENDARIO DE DISPONIBILIDAD

Índice	Abr	May	Jun	Jul	Ago	Sep
NDVI	◑	●	●	●	●	◑
NDMI	○	◑	●	●	●	◑

3 — ANÁLISIS TEMPORAL

Evolución de la Campaña

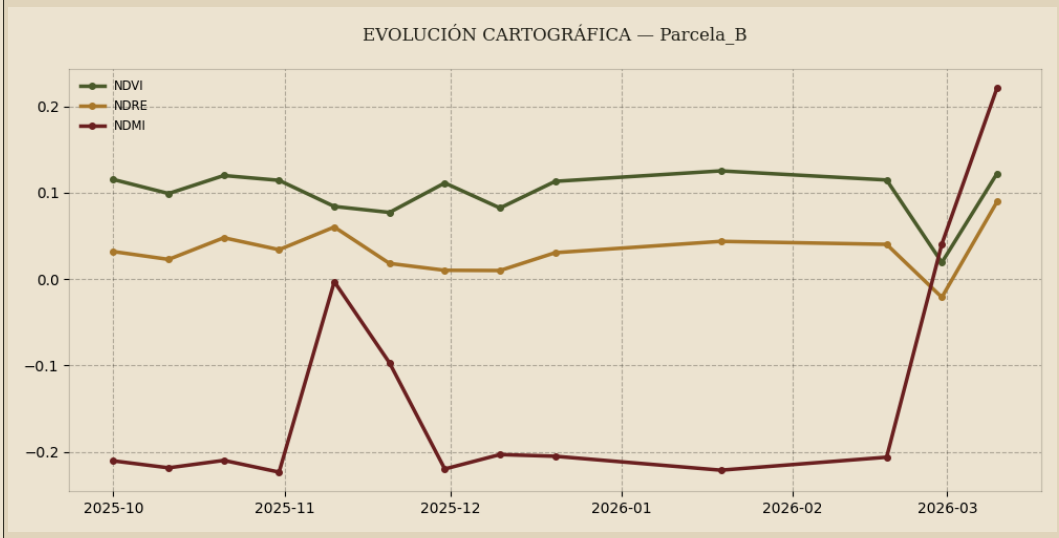

EVOLUCIÓN DE ÍNDICES MMXXV

4 — INTERPRETACIÓN Y RECOMENDACIONES

Dictamen Técnico

ESTADO ACTUAL
Óptimo

TENDENCIA
Estable

Estado vegetativo excelente. Se recomienda mantener monitorización.

5 — METODOLOGÍA Y FUENTES

Ficha Técnica

SATÉLITE	*Copernicus Sentinel-2 (ESA). Resolución 10m. Frecuencia 5 días.*
CARTOGRAFÍA	*Plan Nacional de Ortofotografía Aérea (PNOA) e IGN Base.*
PARCELARIO	*Sistema de Información Geográfica de Parcelas Agrícolas (SIGPAC).*

PRÓXIMA CAPTURA PREVISTA

25/04/2026

FIN