ANÁLISIS GEOESPACIAL

Finca Norte - Tempranillo | ID: Parcela_A

FECHA GENERACIÓN: 22/04/2026
COPERNICUS SENTINEL-2 L2A

1 — LOCALIZACIÓN Y DATOS CATASTRALES

ORTODOTO AÉREA (PNOA)

SIGPAC

DELIMITACIÓN SIGPAC

TOPOGRAFÍA IGN

Altitud Media	450 m	**Superficie**	3.68 ha
Pendiente Máx/Media	4.5% (2.6°)	**Municipio**	Logroño
Orientación Predom.	Sureste (SE)	**Polígono/Parcela**	12/45

2 — ÍNDICES DE VEGETACIÓN DISPONIBLES

VIGOR (NDVI)



CLOROFILA (NDRE)

ESTRÉS HÍDRICO (NDMI)

Calendario de seguimiento óptimo

Índice	Abr	May	Jun	Jul	Ago	Sep
NDVI	◑	●	●	●	●	◑

NDMI	○	◑	●	●	●	◑
NDRE	○	○	●	●	●	◑

ANÁLISIS GEOESPACIAL

Finca Norte - Tempranillo | ID: Parcela_A

FECHA GENERACIÓN: 22/04/2026
COPERNICUS SENTINEL-2 L2A

3 — ANÁLISIS TEMPORAL DE LA CAMPAÑA

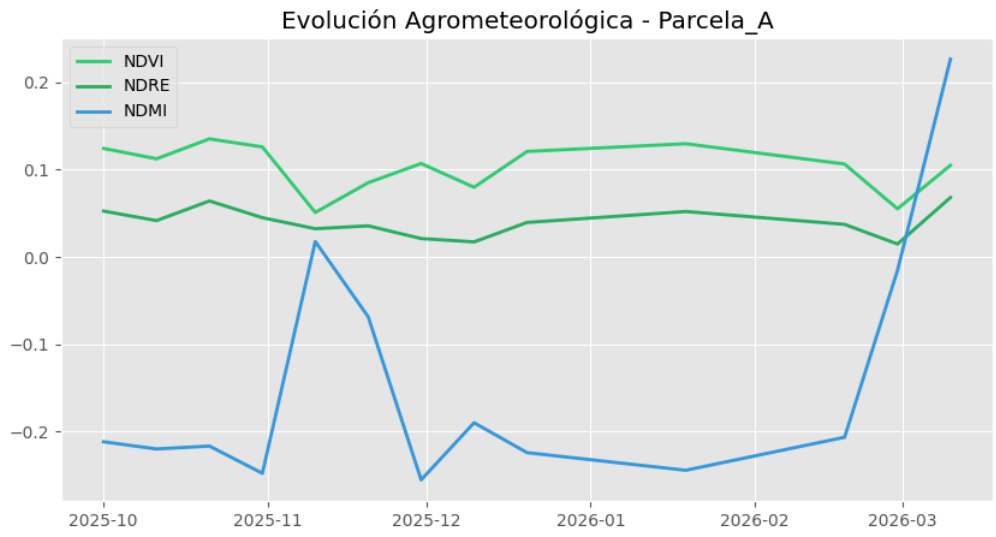

EVOLUCIÓN HISTÓRICA DE ÍNDICES

Nota: Los valores reflejan la media de la parcela en reflectancia corregida atmosféricamente (L2A).

4 — INTERPRETACIÓN Y RECOMENDACIONES

DICTAMEN ACTUAL:

Óptimo

TENDENCIA:

Estable →

Informe técnico:
Estado vegetativo excelente. Se recomienda mantener monitorización.

ANÁLISIS GEOESPACIAL

Finca Sur - Graciano | ID: Parcela_B

FECHA GENERACIÓN: 22/04/2026
COPERNICUS SENTINEL-2 L2A

1 — LOCALIZACIÓN Y DATOS CATASTRALES

ORTODOTO AÉREA (PNOA)

SIGPAC

DELIMITACIÓN SIGPAC

TOPOGRAFÍA IGN

Altitud Media	450 m	**Superficie**	3.68 ha
Pendiente Máx/Media	4.5% (2.6°)	**Municipio**	Logroño
Orientación Predom.	Sureste (SE)	**Polígono/Parcela**	14/02

2 — ÍNDICES DE VEGETACIÓN DISPONIBLES

VIGOR (NDVI)

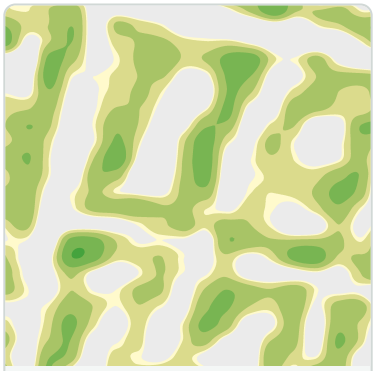

CLOROFILA (NDRE)

ESTRÉS HÍDRICO (NDMI)

Calendario de seguimiento óptimo

Índice	Abr	May	Jun	Jul	Ago	Sep
NDVI	◑	●	●	●	●	◑

NDMI	○	◑	●	●	●	◑
NDRE	○	○	●	●	●	◑

ANÁLISIS GEOESPACIAL

Finca Sur - Graciano | ID: Parcela_B

FECHA GENERACIÓN: 22/04/2026
COPERNICUS SENTINEL-2 L2A

3 — ANÁLISIS TEMPORAL DE LA CAMPAÑA

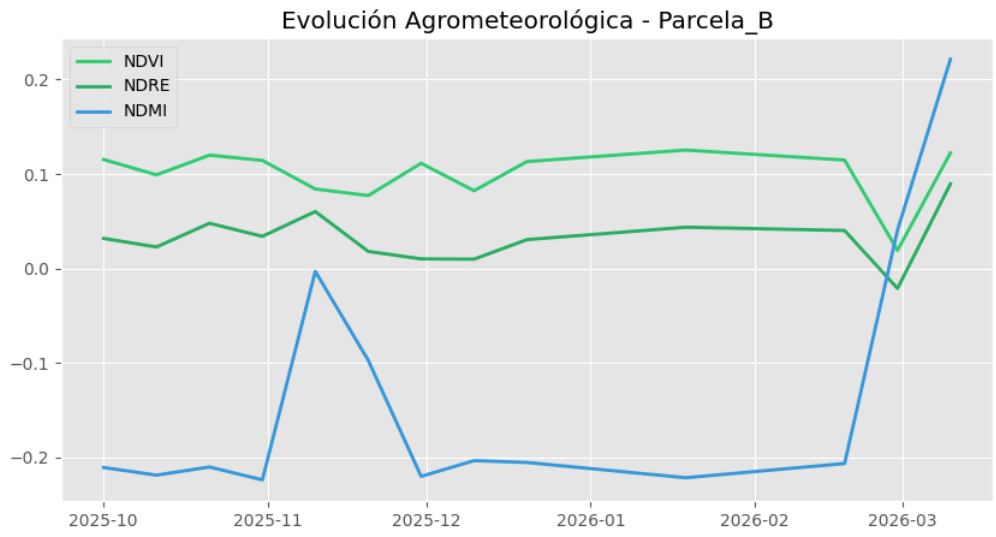

EVOLUCIÓN HISTÓRICA DE ÍNDICES

Nota: Los valores reflejan la media de la parcela en reflectancia corregida atmosféricamente (L2A).

4 — INTERPRETACIÓN Y RECOMENDACIONES

DICTAMEN ACTUAL:

Óptimo

TENDENCIA:

Estable →

Informe técnico:
Estado vegetativo excelente. Se recomienda mantener monitorización.

5 — METODOLOGÍA Y PRÓXIMAS CITAS

Sentinel-2	Imágenes multiespectrales de 10m de resolución corregidas atmosféricamente.
SIGPAC	Geometrías oficiales del Ministerio de Agricultura, Pesca y Alimentación.
PNOA	Fotografía aérea de máxima resolución del Plan Nacional de Ortofotografía Aérea.

PRÓXIMA IMAGEN DISPONIBLE (Previsión)

25/04/2026

* La disponibilidad real depende de la cobertura de nubes y el tiempo de procesado de la ESA.

Este informe es de carácter técnico y se basa en datos abiertos de Copernicus y el IGN. No sustituye la inspección visual en campo.